Platzhalter

Lo
go

Handbuch

Objekterkennung mittels Ultraschallradar

Autor:	Wilko Hinrichs
Matrikel-Nr.:	7026413
Autor:	Simon Müller
Matrikel-Nr.:	7025823
Studiengang:	Maschinenbau
Erstprüfer:	Prof. Dr. Elmar Wings
Zweitprüfer:	Malena Wilken
Abgabedatum:	14. April 2026

Hochschule Emden/Leer · Fachbereich Technik · Abteilung Maschinenbau
Constantiaplatz 4 · 26723 Emden · `http://www.hs-emden-leer.de`

Inhaltsverzeichnis

Abbildungsverzeichnis iii

Tabellenverzeichnis v

1 Wichtige Hinweise vorab 1
1.1 Willkommen . . . 1
1.2 Zu diesem Handbuch . . . 1
1.3 Bestimmungsgemäße Verwendung . . . 1

2 Die Hauptfunktionen 3

3 Geräteübersicht 5

4 Lieferumfang 7
4.1 Anforderungen an die Stromversorgung . . . 7

5 Inbetriebnahme 9
5.1 Aufstellung . . . 9
5.2 Software-Start . . . 9
5.2.1 Visuelle Darstellung: . . . 10
5.2.2 Bedeutung für den Anwender: . . . 10

6 Bedienung und Anzeige 11
6.1 Das Radar-Bild interpretieren . . . 11
6.2 Reichweite . . . 12

7 Pflege und Wartung 13
7.1 Reinigung . . . 13
7.2 Lagerung . . . 13

8 Sicherheitshinweise 15
8.1 Sicherheit im Umgang mit der Energieversorgung . . . 15

9 Fehlersuche 17
9.1 Software-Fehlermeldungen . . . 17
9.1.1 Handlungsanweisung bei Systemfehler . . . 18

10 Spezifikationen 19
10.1 Daten und Energiefluss . . . 19

10.2 Technische Spezifikationen 19

Abbildungsverzeichnis

2.1 Funktionsweise 3

3.1 Übersicht Ultraschallradar 5

5.1 Benutzeroberfläche: System fährt hoch 10

6.1 Benutzeroberfläche 11
6.2 Reichweite 12

9.1 Flussdiagramm: Fehlermeldungen 17
9.2 Benutzeroberfläche: Systemfehler 18

10.1 Daten und Energiefluss des Systems 19

Tabellenverzeichnis

4.1 Übersicht des Lieferumfangs 7

10.1 Technische Spezifikationen des Radarsystems 19

1 Wichtige Hinweise vorab

1.1 Willkommen

Herzlichen Glückwunsch zum Erwerb Ihres neuen Ultraschall-Radarsystems. Dieses Gerät ermöglicht es Ihnen, Hindernisse in der Umgebung rein akustisch zu erfassen und visuell auf einem Bildschirm darzustellen – ganz ähnlich wie bei der Einparkhilfe eines modernen Autos oder dem Radar eines Schiffes.

1.2 Zu diesem Handbuch

Dieses Handbuch führt Sie Schritt für Schritt durch die Bedienung des bereits fertig montierten Systems. Sie benötigen keine Programmierkenntnisse oder elektrotechnisches Vorwissen.

1.3 Bestimmungsgemäße Verwendung

Das System ist für die Verwendung in trockenen Innenräumen konzipiert. Es dient der Demonstration von Objekterkennung und darf nicht für sicherheitskritische Anwendungen (z. B. als echtes Warnsystem an Fahrzeugen) verwendet werden.

2 Die Hauptfunktionen

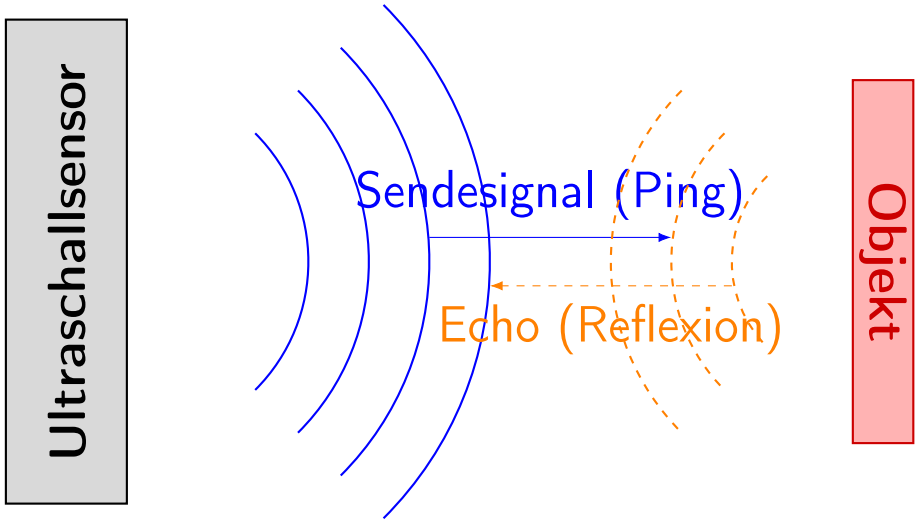

Abbildung 2.1: Funktionsweise

Das Radarsystem arbeitet nach dem Prinzip des „Echo-Lot-Verfahrens“. Hierbei erfüllt das Gerät drei Kernaufgaben vollautomatisch:

1. **Die Suchbewegung:** Die Dreheinheit schwenkt den Ultraschallsensor kontinuierlich in einem Halbkreis (180°). Dadurch wird der gesamte Bereich vor dem Gerät lückenlos überwacht.

2. **Die Messung:** Der Ultraschallsensor sendet für das menschliche Ohr unhörbare Schallimpulse aus. Treffen diese auf ein Hindernis, werden sie zurückgeworfen. Das Gerät misst die Zeit, bis das Echo eintrifft, und errechnet daraus zentimetergenau die Entfernung.

3. **Die Visualisierung:** Diese Daten werden an Ihren Computer gesendet, wo sie in eine grafische Benutzeroberfläche übersetzt werden.

3 Geräteübersicht

In diesem Abschnitt sehen Sie die wichtigsten Bedienelemente und Komponenten Ihres betriebsbereiten Systems.

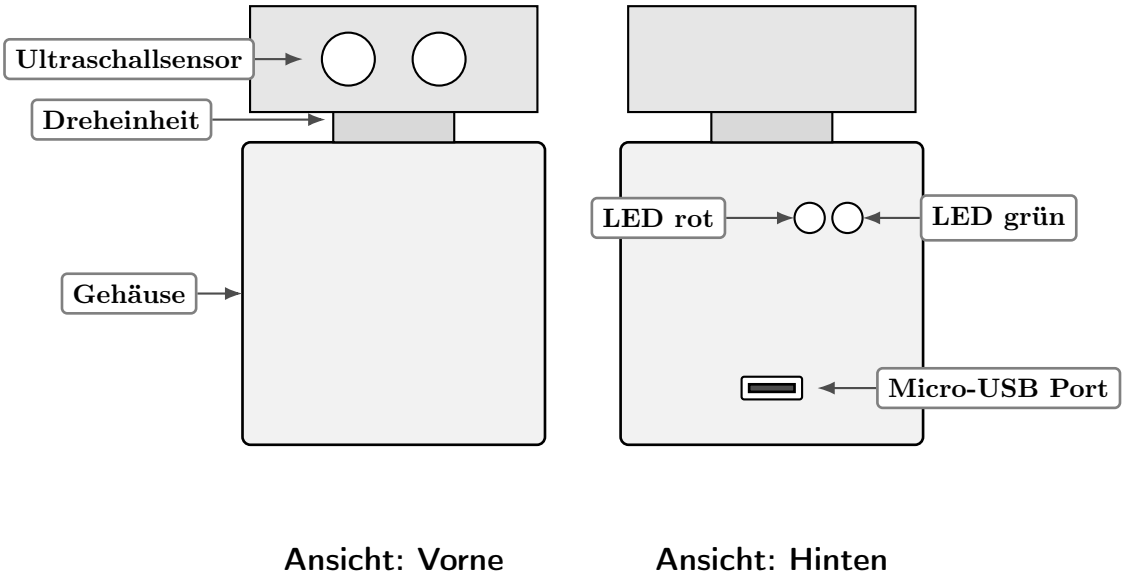

Abbildung 3.1: Übersicht Ultraschallradar

- **Ultraschallsensor:** Hier werden die Ultraschallsignale gesendet und empfangen.
- **Dreheinheit:** Hier ist der Motor verbaut, welcher den Ultraschallsensor dreht.
- **Gehäuse:** Hier ist die Steuerelektronik untergebracht.
- **Micro-USB Port:** Die Verbindung zu Ihrem Computer für den Strom und Datenfluss.
- **LED rot/ LED grün:** Sie dienen der Statusanzeige des Systems im Betrieb und melden eventuelle Fehler.

4 Lieferumfang

Obwohl das Gerät fertig montiert ist, sollten Sie prüfen, ob alle Systemkomponenten unbeschädigt vorhanden sind.

Menge	**Komponente**	**Ausführung / Anmerkung**
1x	Ultraschall-Radarsystem	fertig montierte Einheit auf Gehäuse
1x	USB-Verbindungskabel	Micro-USB auf USB-A
1x	Kurzanleitung	Quick-Start-Guide

Tabelle 4.1: Übersicht des Lieferumfangs

Sollten Teile fehlen, beschädigt sein oder Kabel lose sein, nehmen Sie das Gerät bitte nicht in Betrieb.

4.1 Anforderungen an die Stromversorgung

Für den reibungslosen Betrieb des Radarsystems ist eine stabile Energiequelle und ein konstanter Datenfluss erforderlich. Das System wird ausschließlich über das mitgelieferte USB-Kabel mit Strom versorgt und an den Computer angeschlossen.

- **Anschluss am Gerät:** Micro-B USB (Rückseite des Radarsystems).
- **Anschluss am Computer:** Standard USB-A.
- **Betriebsspannung:** 5 V DC (wird automatisch vom Computer-USB-Anschluss bereitgestellt).
- **Stromaufnahme:** Das System benötigt im Betrieb maximal ca. 1 A (1000 mA).

5 Inbetriebnahme

Da Ihr Radarsystem bereits fertig montiert ist, sind nur wenige Handgriffe für den Start nötig.

5.1 Aufstellung

Platzieren Sie das Radarsystem auf einer ebenen Fläche (z. B. einem Tisch). Achten Sie darauf, dass sich im Umkreis von mindestens 50 cm keine Gegenstände befinden, die die Rotation der Dreheinheit behindern könnten.

5.2 Software-Start

Das Radarsystem wird in Kombination mit einer PC-Software betrieben, die als grafische Benutzeroberfläche (GUI) dient und die Sensordaten in Echtzeit visualisiert.

Schritt 1: Software herunterladen

Um die Software zu beziehen, benötigen Sie lediglich einen Webbrowser.

- Öffnen Sie die Projektseite unter folgendem Link:
  `https://github.com/WH171/Ultraschallradar_Automatisierungstechnik/tree/main/Benutzeroberflaeche_Ultraschallradar_Processing`
- **Für Anwender:** Navigieren Sie auf der GitHub-Seite im rechten Seitenmenü zum Bereich „Releases“. Laden Sie dort die aktuellste gepackte Version für ihr Betriebssystem der Software:
  `Benutzeroberflaeche-Ultraschallradar-Processing` herunter.
- Speicher Sie die heruntergeladene Anwendung an einen beliebigen Ort auf Ihrer lokalen Festplatte (z. B. auf den Desktop).
- **Hinweis:** Es ist keine Installation von Drittsoftware oder einer Entwicklungsumgebung notwendig. Das Programm ist sofort lauffähig.

Schritt 2: Programm starten

Um eine reibungslose Kommunikation zwischen Hardware und Software zu gewährleisten, halten Sie bitte folgende Reihenfolge ein:

1. **Hardware anschließen:** Stellen Sie sicher, dass das Radarsystem über das USB-Kabel mit dem Computer verbunden ist und mit Strom versorgt wird.
2. **Software ausführen:** Navigieren Sie in den zuvor kopierten Ordner auf Ihrem Computer. Führen Sie die ausführbare Programmdatei: Ultraschallradar Benutzeroberfläche App mit einem Doppelklick aus.
3. **System-Initialisierung:** Die Benutzeroberfläche öffnet sich nun automatisch und leitet den Hardware-Selbsttest ein.

5.2.1 Visuelle Darstellung:

Der Bildschirm auf dem Computermonitor ist abgedunkelt. Im Zentrum erscheint gut lesbar die Meldung: *„System fährt hoch... Hardware-Selbsttest wird durchgeführt."*

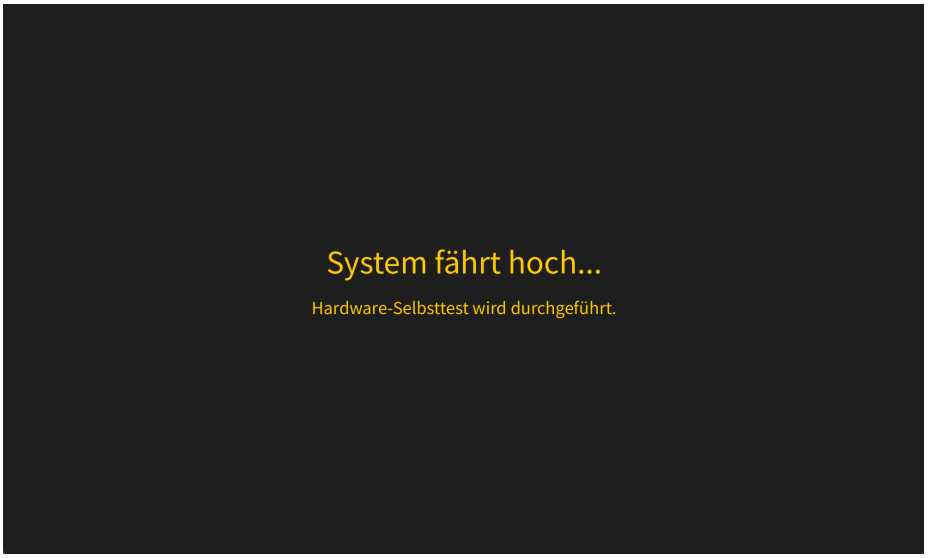

Abbildung 5.1: Benutzeroberfläche: System fährt hoch

5.2.2 Bedeutung für den Anwender:

Das System prüft die interne serielle Kommunikation, fährt den Servomotor in die definierte Ausgangsposition (0°) und sendet einen ersten Test-Ultraschallimpuls, um Hardware- oder Kabelbrüche auszuschließen. Der Benutzer muss in dieser Phase keine Eingaben tätigen, sondern lediglich warten. Am Gehäuse der Hardware leuchten zur visuellen Bestätigung kurz beide LEDs (Grün und Rot) auf.

6 Bedienung und Anzeige

6.1 Das Radar-Bild interpretieren

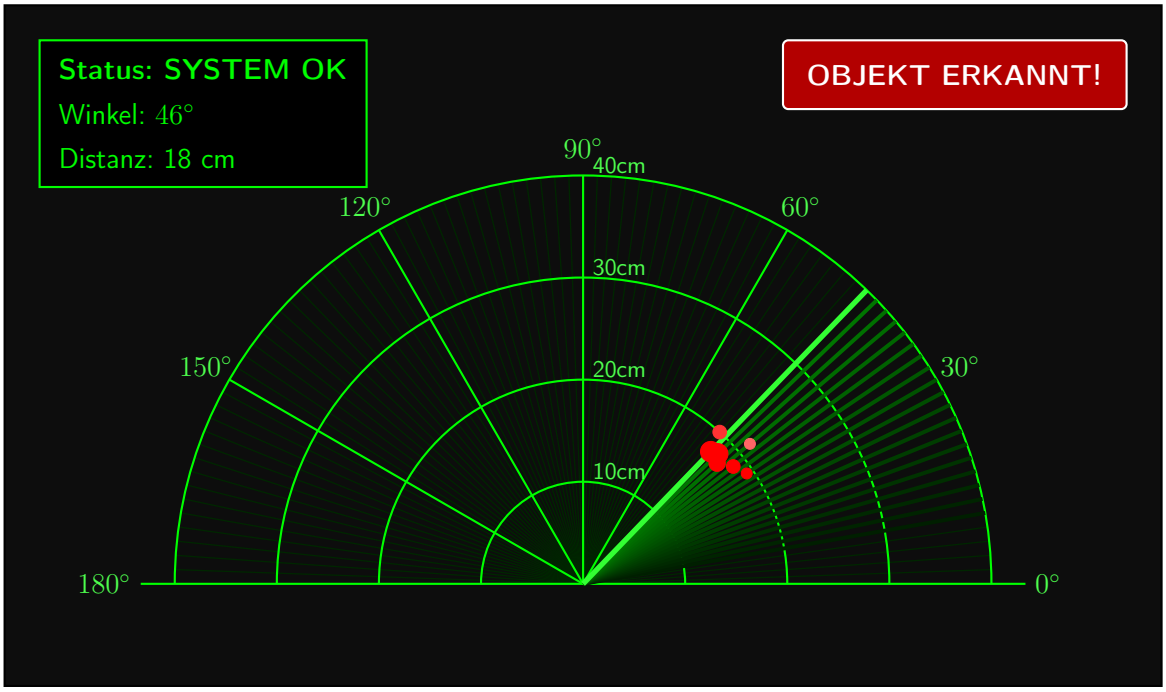

Abbildung 6.1: Benutzeroberfläche

Nach bestandenem Selbsttest wechselt das System automatisch in den Normalbetrieb. Die grüne Status-LED am Gehäuse leuchtet nun dauerhaft.

Auf Ihrem Bildschirm sehen Sie eine kreisförmige Anzeige.

- **Visuelle Darstellung:** Das Zentrum der Benutzeroberfläche bildet ein Radar-Gitter in Form von Halbkreisen mit festen Abstands- und Winkelmarkierungen. Ein optischer Scan-Strahl bewegt sich im Halbkreis stufenlos von 0° auf 180° und wieder zurück.

- **Hindernisse:** Erkannte Hindernisse werden als rote Punkte auf dem Gitter eingezeichnet.

6.2 Reichweite

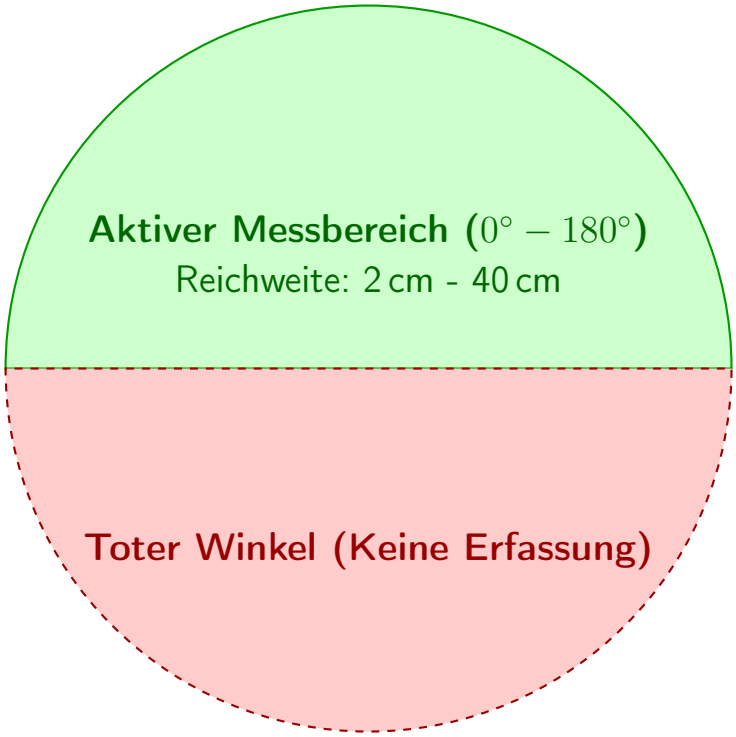

Abbildung 6.2: Reichweite

In der oberen linken Ecke der Benutzeroberfläche befindet sich die Statusanzeige. Sie zeigt den aktuellen Systemstatus („*SYSTEM OK*"), den exakten aktuellen Scan-Winkel in Grad sowie die berechnete Distanz zum nächsten Objekt in Zentimetern an. Das System erkennt Objekte zuverlässig in einer Distanz von ca. $2\,cm$ bis $40\,cm$.

7 Pflege und Wartung

7.1 Reinigung

Halten Sie die beiden runden Öffnungen des Ultraschallsensors sauber und trocken. Staub kann vorsichtig mit einem trockenen Tuch oder einem Pinsel entfernt werden. Verwenden Sie niemals Wasser oder Reinigungsmittel direkt auf der Elektronik.

7.2 Lagerung

Lagern Sie das Gerät bei Nichtgebrauch an einem staubfreien trockenen Ort. Achten Sie darauf, dass die Kabel nicht geknickt werden.

8 Sicherheitshinweise

Bewegliche Teile: Greifen Sie während des Betriebs niemals in die Dreheinheit. Der Motor hat zwar eine geringe Kraft, dennoch können Kabel abgerissen oder die Mechanik beschädigt werden.

- Betreiben Sie das Gerät nur über einen standardkonformen USB-Port ($5\,V$).
- Halten Sie das Gerät fern von Flüssigkeiten.

8.1 Sicherheit im Umgang mit der Energieversorgung

- Verwenden Sie ausschließlich Netzteile, die der CE-Norm entsprechen und eine stabilisierte Ausgangsspannung von $5\,V$ liefern.
- Schließen Sie das Gerät niemals an Netzteile mit variabler Spannung an, da Spannungsspitzen über $5,5\,V$ die Elektronik (Arduino und Sensor) dauerhaft zerstören können.
- Trennen Sie das Netzteil bei längerer Nichtbenutzung oder bei Gewitter von der Steckdose.

9 Fehlersuche

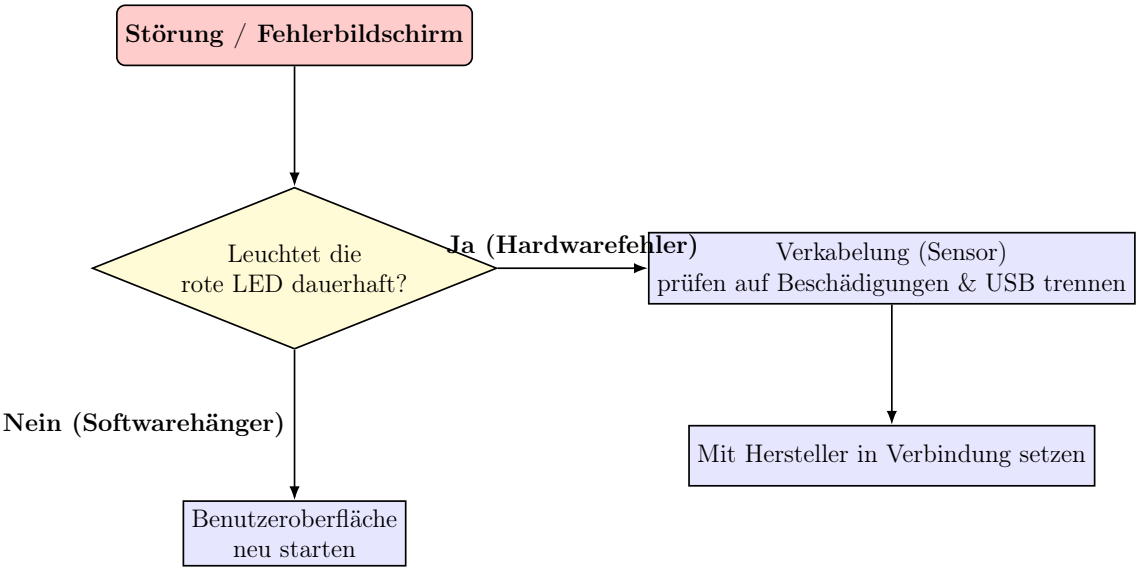

Abbildung 9.1: Flussdiagramm: Fehlermeldungen

9.1 Software-Fehlermeldungen

Sollte während des Selbsttests oder im laufenden Betrieb ein kritischer Hardwarefehler auftreten, erscheint eine Meldung. Alle motorischen Bewegungen des Servos werden sofort gestoppt.

- **Visuelle Darstellung:** Die Benutzeroberfläche wechselt auf einen warnenden, roten Hintergrund mit Warnhinweisen. Das Radarbild wird komplett ausgeblendet.
- **Fehlermeldung:** *„ SYSTEMFEHLER - Sicherstellen das der Computer mit dem radarsystem verbunden ist! - Anlage überprüfen und Arduino neustarten.”*
- **Hardware-Indikator:** Am Gehäuse des Radarsystems leuchtet die rote LED dauerhaft auf.

Abbildung 9.2: Benutzeroberfläche: Systemfehler

9.1.1 Handlungsanweisung bei Systemfehler

1. **Stromversorgung trennen:** Die Anlage stromlos machen (USB-Verbindung zum Computer trennen).
2. **Sichtfeld kontrollieren:** Sicherstellen, dass das Sichtfeld des Sensors beim Starten nicht direkt auf 0 cm blockiert ist.
3. **Neustart:** Die USB-Verbindung wiederherstellen und die Benutzeroberfläche neu starten, um den Selbsttest erneut zu initiieren.

10 Spezifikationen

10.1 Daten und Energiefluss

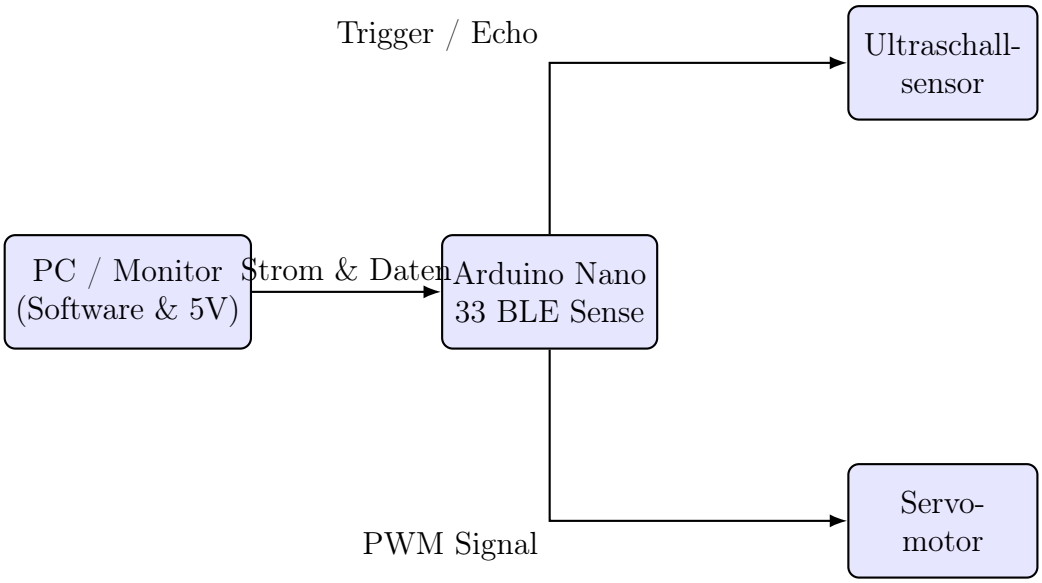

Abbildung 10.1: Daten und Energiefluss des Systems

10.2 Technische Spezifikationen

Parameter	**Wert**
Abmessungen (B × T × H)	80 × 80 × 100 mm
Betriebsspannung	5,0 V DC (über USB)
Stromanschluss	Micro-B USB
Interne Steuereinheit	Arduino Nano 33 BLE Sense
Betriebstemperatur (empfohlen)	0 °C bis 40 °C

Tabelle 10.1: Technische Spezifikationen des Radarsystems